Informa Perú

INSTITUCIONES DE MICROFINANZAS

Optimiza tus recursos, controla el trabajo en campo y aumenta el nivel de satisfacción de tus clientes

NAVEGO 360

Plataforma web mapping

especializada en la planificación, despacho y monitoreo del trabajo en campo.

PRINCIPALES BENEFICIOS

Disminuye costos operativos

Eliminando procesos manuales, reduciendo tiempos muertos y horas extras innecesarias

Planifica rutas óptimas de trabajo

Usando inteligencia artificial pensada en situaciones de la vida real

Monitoreo de personal en campo

Conoce la ubicación en tiempo real de cada uno de ellos

Ejecuta mejores estrategias de trabajo

Usando herramientas digitales con acceso desde su celular

Dale poder de negociación a tus vendedores

Poniendo a su disposición herramientas de consulta en línea

MEJORAMOS

TU EXPERIENCIA DE TRABAJO EN CASA Y EN LA OFICINA

Planifica, organiza y distribuye el trabajo en campo

Monitorea en tiempo real las incidencias

Con la **información** obtenida en campo, personaliza reportes

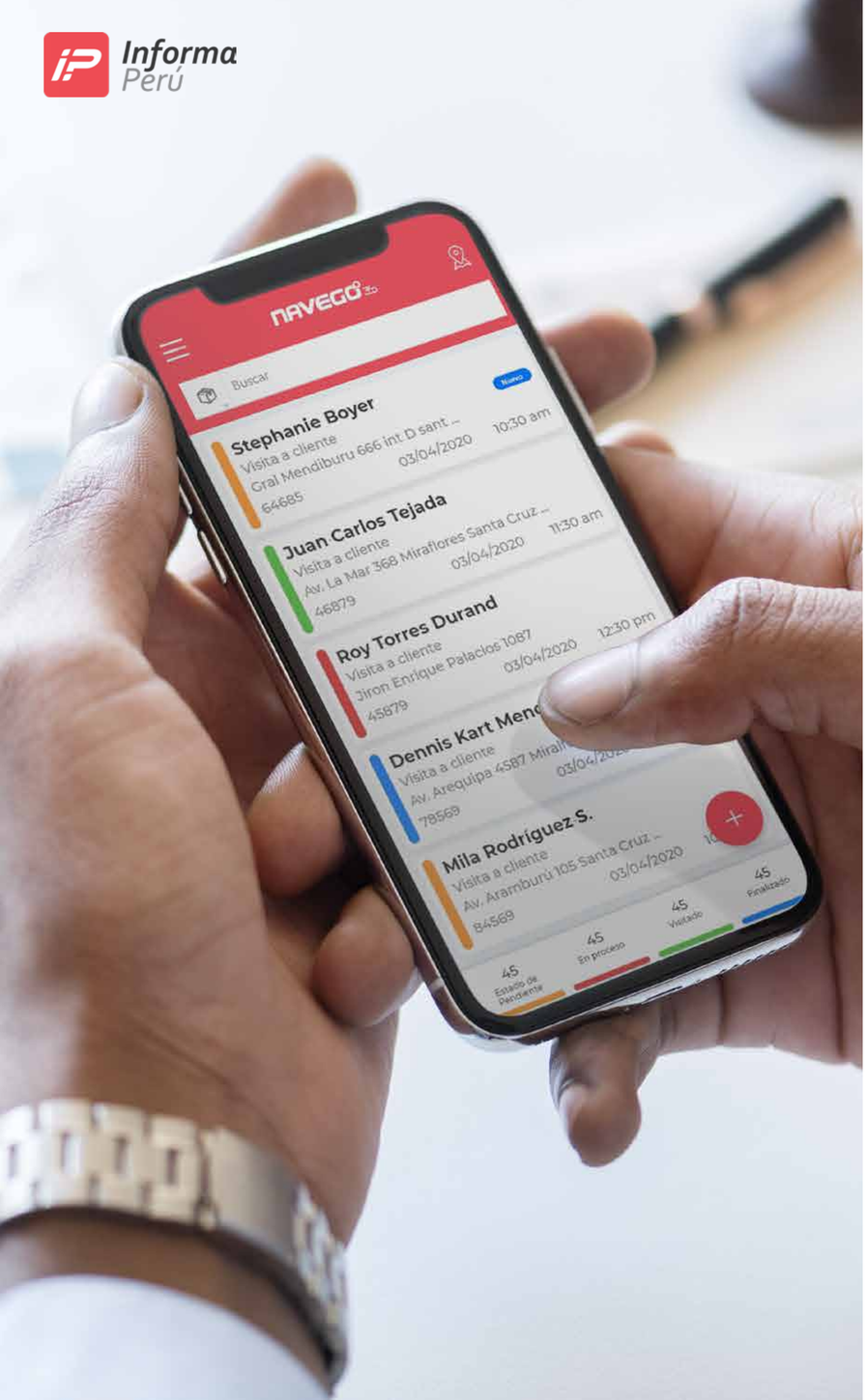

FACILITA
LA FORMA DE TRABAJAR EN CAMPO

Obtén información rica como Leads(POI) y compañeros de trabajo

Registra información y envíala por un solo canal de comunicación

Digitalización de documentos, cero papel

DEMOSTRACIONES

Tracking y funcionalidades

Atención de tareas de campo

Reportes y API´s para desarrolladores

VENTA

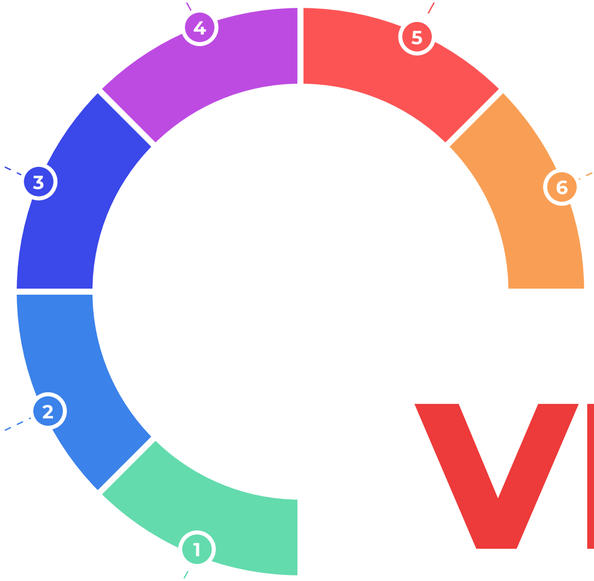

Centrales de riesgo

La conexión con centrales de riesgo estará disponible en los dispositivos móviles y en la plataforma web de la institución de manera

Trabajo en campo

El personal de trabajo en campo tendrá herramientas configuradas a medida que le permitirán iniciar y terminar el proceso de venta de productos financieros de manera ágil y segura. El trabajo en campo podrá ser auditado y monitoreado en tiempo real

Ruteo

Procesamos las mejores rutas y las asignamos a los móviles del personal en campo, lo que permite planificar las visitas a clientes de manera ordenada, simple y con alta probabilidad de éxito. Hemos considerado además las zonas de alto contagio de COVID-19 como una variable de riesgo al momento de generar una nueva ruta

Georeferenciacion de cartera

Los servicios de normalización y georeferenciación de toda la cartera de clientes son el punto de partida sobre el cual se podrán trabajar todas las estrategias de venta y cobranza

Proceso de aprobacion

Los procesos de aprobación y desaprobación se realizarán desde interfaces web disponibles en la nube por medio de expedientes digitales en formato PDF que contienen toda la información registrada en los aplicativos móviles al momento de la visita en campo, los indicadores emitidos por las centrales de riesgo y las bases de datos históricas

Desembolso

Digitalizamos el proceso de aprobación de créditos y nos aseguramos que toda operación aprobada emita una orden de desembolso a los sistemas centrales de la institución, además de notificar al cliente vía SMS o correo electrónico que tiene un préstamo aprobado

POST VENTA

Proceso de notificación al equipo comercial que permite tener rutas orientadas a la visita de clientes con riesgo potencial de morosidad y rutas orientadas a la venta nueva (penetración de clientes)

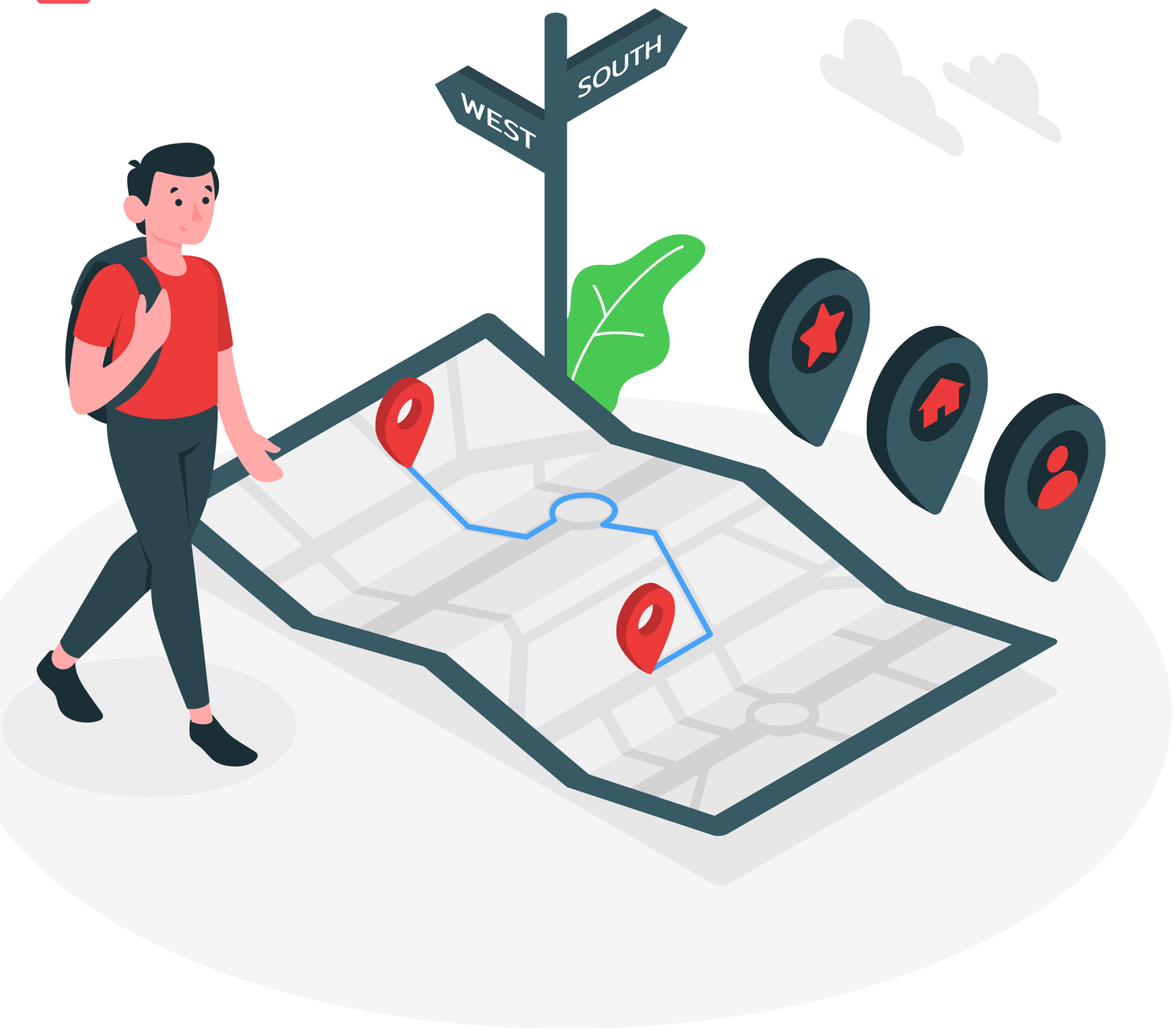

COBRANZA

Planificación de rutas de cobranza basadas no solo en el monto de la deuda, el tipo de cliente, la ubicación geográfica, sino además en la más alta probabilidad de cobranza. Todas estas variables juntas hacen que su labor de cobranza sea la más acertada

REPORTES PERSONALIZADOS

NOS ADAPTAMOS A LO QUE NECESITES

En base a toda la información registrada en campo, Navego 360 te permite personalizar múltiples tipos de reportes en diferentes formatos:

POWER BI **PDF** **EXCEL**

y muchos más

Informa Perú

www.informaperu.com

servicioalcliente@informaperu.com

Central telefónica
(511) 3140110

TargetMaps

Los datos, textos e imágenes contenidos en el documento tienen carácter de confidencial, y son de uso exclusivo de TargetMaps, sus clientes y sus partners autorizados. Queda prohibida cualquier distribución, divulgación o reproducción completa o parcial. En caso no esté autorizado a poseer este material, por favor enviar un correo electrónico a contacto@targetmaps.pe